STT-NF

Praktikum SIG
Aplikasi Google Map 1

TEKNIK INFORMATIKA / SISTEM INFORMASI

STT TERPADU NURUL FIKRI

Praktikum Mandiri 2

1. Buat topik manajemen map lokasi di Kota Depok dan sekitarnya menggunakan Google Map dengan topik sebagai berikut (minimal ada 8 lokasi)
    a. Taman kota
    b. Setu atau waduk seputar kota Depok (jika ada di perbatasan depok dapat dimasukan)
    c. Rumah sakit / Puskesmas
    d. Lapangan olah raga / GOR
2. Screenshot hasilnya peta anda tampilkan didalam laporan ini

1. Taman Kota

Longitude : 106.817364
Latitude : -6.3936813

2. Setu Cilodong

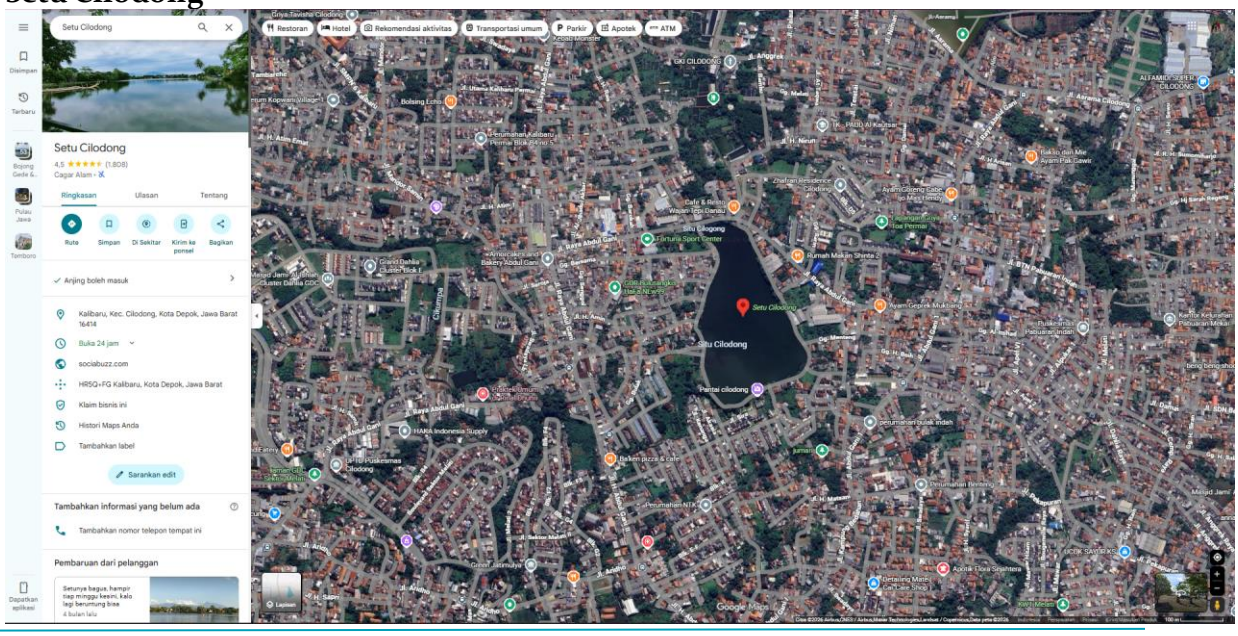

Longitude : 106.8361911
Latitude : -6.441341

3. **Setu Tujuh Muara**

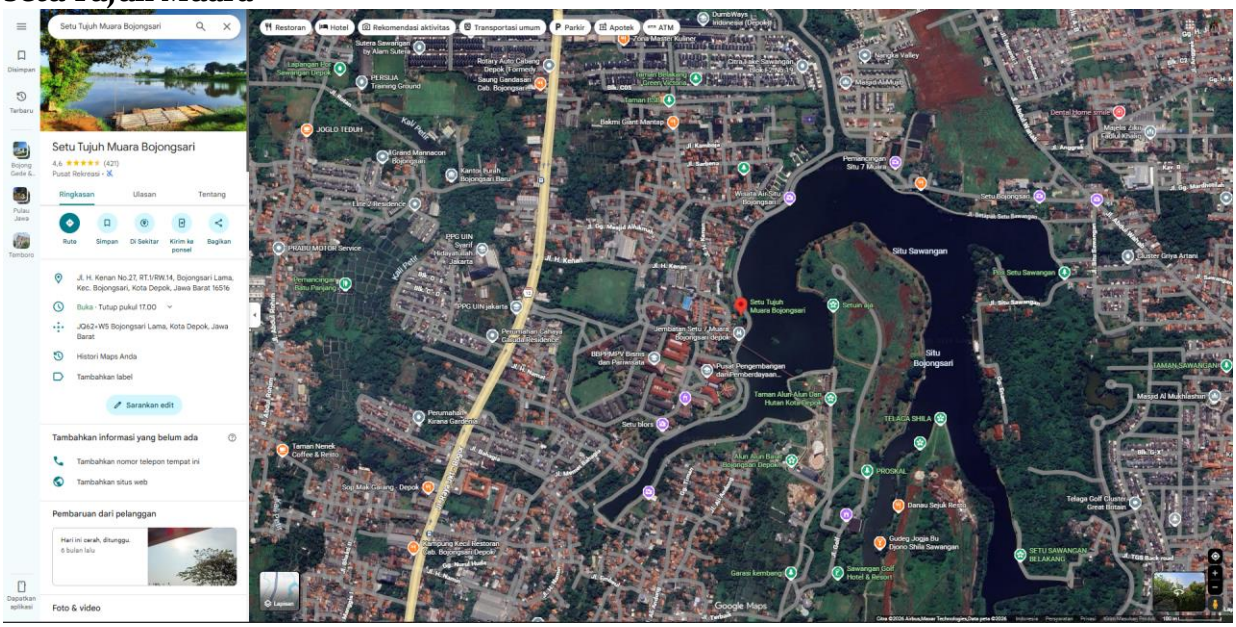

Longitude : 106.7478495
Latitude : -6.3877063

4. **Setu Pengasinan**

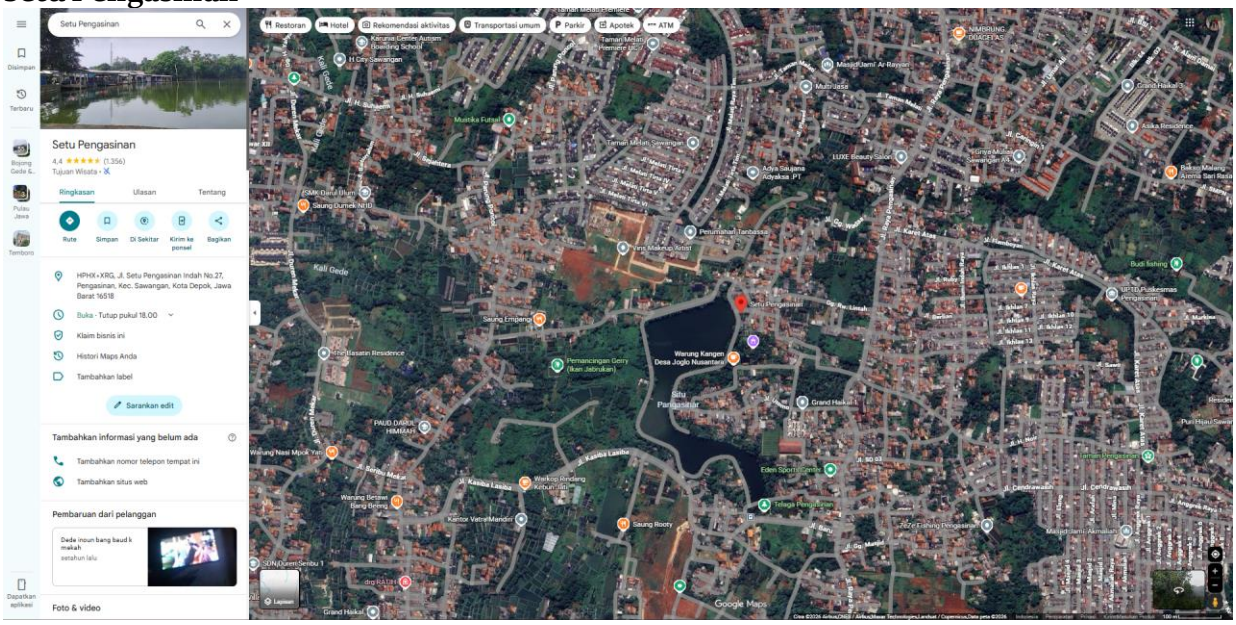

Longitude : 106.7473468
Latitude : -6.4206933

5. **Situ Rawa Besar**

Longitude : 106.8143117
Latitude : -6.3916295

6. **GOR Kota Depok**

Longitude : 106.8272989
Latitude : -6.4227307

7. **RS Bhakti Yudha**

Longitude : 106.8036858
Latitude : -6.3977323

8. **RS Citra Arafiq Kelapa Dua**

Longitude : 106.8412652
Latitude : -6.3729065